右手系：中指永远是Z轴

2.1 地球的运转

$F=G\frac{Mm}{r^2}$ →
- 地球与太阳和月球：$F_{日}+F_{月}$(不变)：25800″, 23.5°, 50.3″ → 岁差
- 地球与刚体内部的结构：$F_{日}+F_{月}$(变化)：18.6Y, 9.21″ → 章动
  - m分布不均匀 → 旋转轴变化 → 极移
  - r分布不均匀 → 旋转速度变化 ±1S → 日长变化 ERP EOP

影响

O → Z → X → Y（右手系）　天球/地球坐标系 定义顺序

时间定义条件：连续、简明稳定、可观测　2.2 时间系统

- 以地球自转为基础
  - 恒星时 ST（春分点）
  - 平太阳时 MT（春分点）
  - 世界时 UT（触发于格林尼治）
- 以地球公转为基础
  - 历书时 ET（过春分点）
  - 力学时 DT（大太阳系质心力场的TDB；地球质心力场的TDT）
- 以物质运动为基础
  - 原子时 AT
  - 国际原子时 TAI
  - 协调世界时 UTC（跳秒）

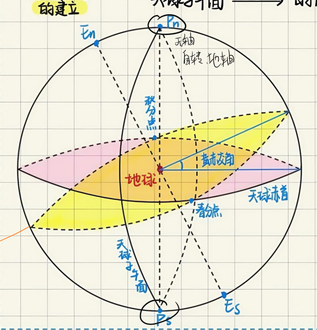
2.3 坐标系统

看分点，与赤分点交点

地球原点 → $\overrightarrow{OP_n}$ ⊥ 天球赤道面 → 23.5° 黄道面

天球坐标系的建立

天球子午面 旋转 → 时圈



$\begin{bmatrix}X\\Y\\Z\end{bmatrix}_{CIS}$ —岁差 Z→ $\begin{bmatrix}X\\Y\\Z\end{bmatrix}_{MT}$ —章动 Z→ $\begin{bmatrix}X\\Y\\Z\end{bmatrix}_{t}$ —极移 E→ $\begin{bmatrix}X\\Y\\Z\end{bmatrix}_{CTS}$

- 协议天球
- 瞬时平天球（历元尺度；还包含可观测）
- 瞬时真天球（N 为CAST；看分点、格林尼治为X轴方向）
- 协议地球（天球坐标系与地球坐标系的转换）

地球坐标系 定义（要素）：原点、尺度、定向

- 几何中心
- 质心
- 参考子午面
- 参考赤道面

历元归算（速度场）　框架转换（七参数）

$ITRFxx(t) \Rightarrow ITRFyy(2000.0)$

- 全球：(a, α) + O + z + x
- 局部：(a, α) + O + z + x + P：BJ54、GD2000、BJ54新

WGS-84, ITRS, CGCS2000　地心地固坐标系　参心坐标系　地心Mn坐标系（N, E, U）

测站中心P + 法线/垂线U + 北方向N　右手系

第3章 地球重力场及地球形状的基本理论　20233021411144 (24.12.26)

物体属性：质量 m　运动 w

3.2 地球重力场基本原理

保守力　做功与路径无关

引力 $F=\frac{GMm}{r^2}+$ 离心力 $F=m\omega^2\rho$ = 重力

保守做功 = 终点位 − 起点位 = 起点位能 − 终点位能

位 = −位能　质点m取单位质量

引力位 $V=G\frac{M}{r}+$ 离心力位 $Q=\frac{1}{2}\omega^2(x^2+y^2)$ = W 重力位

（转化位置 等效值；位于参考面则为0）

位于参考面则为0 保守力作用所性质m位能的改值

方向导数 $\frac{\partial W}{\partial l}=g_l=g\cos(g,l)$

投影到任意方向l　$g=\sqrt{g_x^2+g_y^2+g_z^2}$

偏导 $g_x=\frac{\partial W}{\partial x}$, $g_y=\frac{\partial W}{\partial y}$, $g_z=\frac{\partial W}{\partial z}$

两个特殊方向：
- $g \perp l$：共面90° → $\cos(g,l)=0$ → $\frac{\partial W}{\partial l}=0$ → W是常数 → 重力等位面
- $g \parallel l$：共面180°（常用铅垂线方向） → $\cos(g,l)=-1$（出现原因） → $dl=-\frac{dW}{g}$ → $l_2-l_1=-\frac{W_2-W_1}{g}$



证：两水准面不平行。

对于 $\overrightarrow{AC}$：$W_2-W_1=-g_A(H_C-H_A)=-g_A h_{AC}$

对于 $\overrightarrow{BD}$：$W_2-W_1=-g_B(H_D-H_B)=-g_B h_{BD}$

若两水准面平行，则 $h_{AC}=h_{BD} \Rightarrow g_A=g_B$（不成立）

水准面之间不平行

水准测量闭合环线 存在 "理论闭合差"

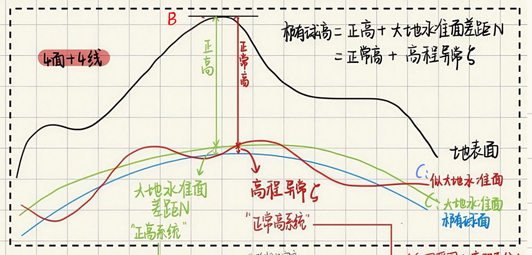
重力对理论质量系统引力重力加速度

- 伽加（Gal = $10^{-2}ms^{-2}=cms^{-2}$）
- 毫伽加（mGal = Gal/1000 = $10^{-5}ms^{-2}$）
- 微伽加（μGal = mGal/1000 = $10^{-8}ms^{-2}$）

地球重力位计算公式：$W=G\int_M\frac{dm}{r}+\frac{\omega^2}{2}(x^2+y^2)$

实际应用中 dm, x, y 无法精确获取，故引入

	离散值	连续值	近似
地球重力位	=	正常重力位	+ 扰动位
重力	=	正常重力	+ 重力异常



椭球球高 = 正高 + 大地水准面差距N
= 正常高 + 高程异常ζ

$dh=-\frac{dW}{g}$ 积分式 $H_{正}=\frac{1}{\bar{g}}\int_c^B g\,dh$

$\bar{g}$ 是B点垂线上的平均重力

平均重力 $\bar{g}$ 无法精确获取 用正常重力公式代替

$H_{正}=\frac{1}{\gamma}\int_c^B g\,dh$（我国采用1956高程系统）

γ 为公式计算

3.3 高程系统

$dW_{Bc}=g_B\,dh_{Bc}$ → $\Delta h_{BB_1}=\frac{1}{g_B}\int_{B_1}^{B}g\,dh$

$dW_{B_1c}=g_{B_1}dh_{B_1c}$ → $\Delta h_{BB_2}=\frac{1}{g_{B_1}}\int_{B_2}^{B_1}g\,dh$

$dW_{B_2c}=g_{B_2}dh_{B_2c}$

$dW_{Bnc}=g_{Bn}dh_{Bnc}$

$dW_{cc}=g_c\,dh_{cc}$ → $\Delta h_{cc}=\frac{1}{g_c}\int_{c}^{c}g\,dh$

累加 $\Delta h_{BB_1}+\Delta h_{BB_2}+\cdots+\Delta h_{Bnc}=\frac{1}{g_B}\int_{B_1}^{B}g\,dh+\frac{1}{g_{B_1}}\int_{B_2}^{B_1}g\,dh+\cdots+\frac{1}{g_{Bn}}\int_{c}^{Bn}g\,dh$

我国高程起算依据
- 水准原点：青岛观象山 | 1956年黄海高程系统：72.289m；1985国家高程基准：72.260m
- 水准零点：青岛银海大世界

第4章 地球形体与地球数学投影的基本理论

20233021411144 (24.12.26)

基本关系：基本式子

几何参数
- 线元素：a, b
- 比例元素：α, e, e′

辅助函数
- c
- W, V（曲率半径）
- t, η^2（大地主题解算）

关系：$c>a>b$；$V>W$；$e'>e$

大椭：小椭 $\sqrt{1+e^2}$；小椭：大椭 $\sqrt{1-e^2}$

$a=b\sqrt{1+e^2}$，$b=a\sqrt{1-e^2}$

$e'=e\sqrt{1+e^2}$，$e=e'\sqrt{1-e^2}$

$e^2=2\alpha-\alpha^2$ 或 2α

空间直角坐标系：XYZ

大地坐标系：BLH（第3章）

大地极性坐标系：SA

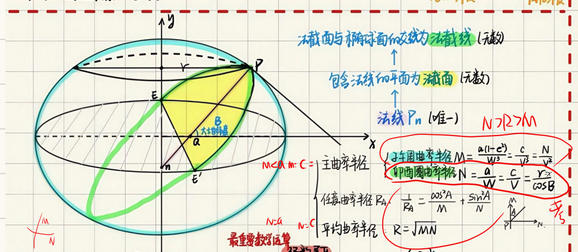
"大地纬度"

B=C → 平行圈（圆）

L=C → 子午圈（椭圆）{(L, x, y)；(L, ρ, γ) → (L, α, u)}

"地心纬度"　"归化纬度"

B > u > p



法截面与椭球面的交线为法截线（弧）

包含法线和平面为法截面（无数）

法线 P_n（唯一）

N>R>M

主曲率半径 $N=\frac{a}{W}=\frac{c}{V}=\frac{N\cos^2B}{c}$

子午圈曲率半径 $M=\frac{a(1-e^2)}{W^3}=\frac{c}{V^3}=\frac{N}{V^2}$

卯酉圈曲率半径 $N=\frac{a}{W}=\frac{c}{V}=\frac{V^2c}{\cos^2B}$

任意曲率半径 P_A：$\frac{1}{P_A}=\frac{\cos^2A}{M}+\frac{\sin^2A}{N}$

平均曲率半径 $R=\sqrt{MN}$

最重要数学运算

N=M N=C

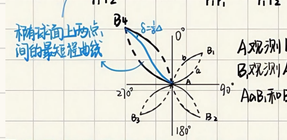
弧长
- 子午圈 / 平行圈 / 大地线 P_1P_2
- 椭圆 / 圆

拟微分 → $dS=R(B)\,dB$

$S=r\Delta l=N\cos B\Delta L$

子午圈 $P_1P_1'^2$ + 平行圈 $P_1'P_2^2$

椭圆 → $R(\sin^2B)$；圆 → $R(\cos^2B)$



椭球面上两点，间的最短程地线

A观测 B_1，AoB，B_1为A的正法截弧，B的反法截弧

B观测 A，BoA，A为B的正法截弧，A的反法截弧

AoB和BoA叫做 A_1B_1 两点的相对法截弧

不规则地球表面

- 长度 → 两项改正 → S
- 方向 → 三差改正 → A

→ 规则椭球面

垂线偏差改正　标高差改正　截面差改正　δ=0

正算（定位）	反算（导航）
$(B_1,L_1)+S_{12}+A_{12}$ → $(B_2,L_2)+A_{21}$	$(B_1,L_1)+(B_2,L_2)$ → S_{12}, A_{12}, A_{21}

方法一：勒让德级数法

大地线微分方程 $\begin{cases}dB=f_1(ds)\\dL=f_2(ds)\\dA=f_3(ds)\end{cases}$ 微分→积分 / 积分→级数

$B_2-B_1=\int_0^S f_1\,ds$ → $B_2=B_1+\frac{S}{\rho}\cos A_1-\frac{S^2}{2\rho^2}\sin^2A_1\tan B_1+\cdots$

→ $L_2=L_1+\frac{S}{\rho}\sin A_1\sec B_1+\cdots$

→ $A_2=A_1\pm\frac{S}{\rho}\sin A_1\tan B_1\pm\cdots$

方法二：高斯平均引数法　关键：$S\to\frac{S}{2}$

重要思想：$P_1\to P_2$：$\int_0^S$ { $M\to P_2$：$\int_0^S$；$M\to P_1$：$\int_0^{-S}$ } 右左级数积分截断误差

$M=\frac{S}{N}$ → $m=\frac{1}{2}(B_1+B_2)$ "平均纬度"　平均纬度不准确

迭代

方法三：球面：$(\varphi_1,\lambda_1)+\delta_{12}+\alpha_{12}$ → $(\varphi_2,\lambda_2)+\alpha_{21}$

① 白塞尔大地主题解算　② 正算

椭球面：$(B_1,L_1)+S_{12}+A_{12}$ → $(B_2,L_2)+A_{21}$

长度投影　方向投影　坐标投影

平面：$(x_1,y_1)+S_{12}+\alpha_{12}$ → $(x_2,y_2)+\alpha_{21}$

高斯投影必须满足的三个条件：

正算	反算
中央子午线投影后为直线 → 确定奇偶函数	← x轴为投影成中央子午线
正形投影条件 → 系数递推公式	← 正形投影条件
中央子午线投影后长度不变 $m_0=$ 子午线弧长X → 确定系数初项	← x轴上的长度投影后保持不变 $m_0=$ 原点纬度 Bf

要满足

长度比 $m=\left\{\begin{matrix}\text{投影面上长度}\\\text{原面上长度}\end{matrix}\right.$ 满足：$m^2=F(q,L)$

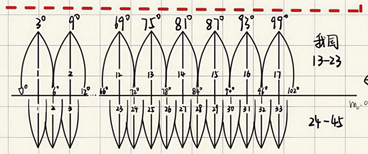
柯西-黎曼条件：$\frac{\partial(x,y)}{\partial(q,L)}=\frac{\partial(q,L)}{\partial(x,y)}$

"投量纬度" $q=\int_0^B\frac{M\,dB}{N\cos B}$

	相对位置	形状	变形
高斯投影	横轴	切椭球圆柱	无角
UTM投影	横轴	割椭球圆柱	无角
兰勃托投影	正轴	圆锥	无角

所有投影都可类比写出三个必须满足的条件

仅白塞尔投影



地面 → 椭球面 → 高斯平面

测量方法：
1. 传统
   - 三角网：前方几何描
   - 导线：灵，但精度比角，结构相对简单
   - 边角网：综合
2. 天文

仪器	z	正比	前后相距
	零点		偏个测站
环境	环境		后前前后